GEOGRAFIA

Simple

DOMENICO RUFFA

mge

GEOGRAFIA

Simple

DOMENICO RUFFA

mge

Conoscere e Rappresentare il TERRITORIO

Il territorio

Si possono conoscere aspetti naturali, clima et aspetti antropici con le Carte geografiche.

Reticolo

Il reticolo geografico si può vedere sun mappamondo o sulla carta geografica del globo.

Clima

Ci sono grandi fasce climatiche sul mondo.

LE MONTAGNE

VALLI GLACIALI
A U

VALLI FLUVIALI
A V

I VULCANI



SPIEGO

Un vulcano è un'apertura della crosta terrestre che dal cratere "sputa" la lava. Prima è magma all'interno poi lava

I TERREMOTI

La crosta terrestre ha delle placche. L'Italia è nella euroasiatica e nell'africana. Se le placche si muovono troppo, si fa un terremoto

ESERCIZIO: COLLEGA I PASSAGGI ALL'IMMAGINE

NASCONDITI SOTTO LA PORTA O UN TAVOLO

STAI LONTANO DA MARE, CASE E PALAZZI

NON USARE L'ASENSORE E NON PRECIPITARTI SULLE SCALE.

QUANDO FINISCE, ESCI CON CALMA DI CASA E STAI LONTANO DA COSTRUZIONI

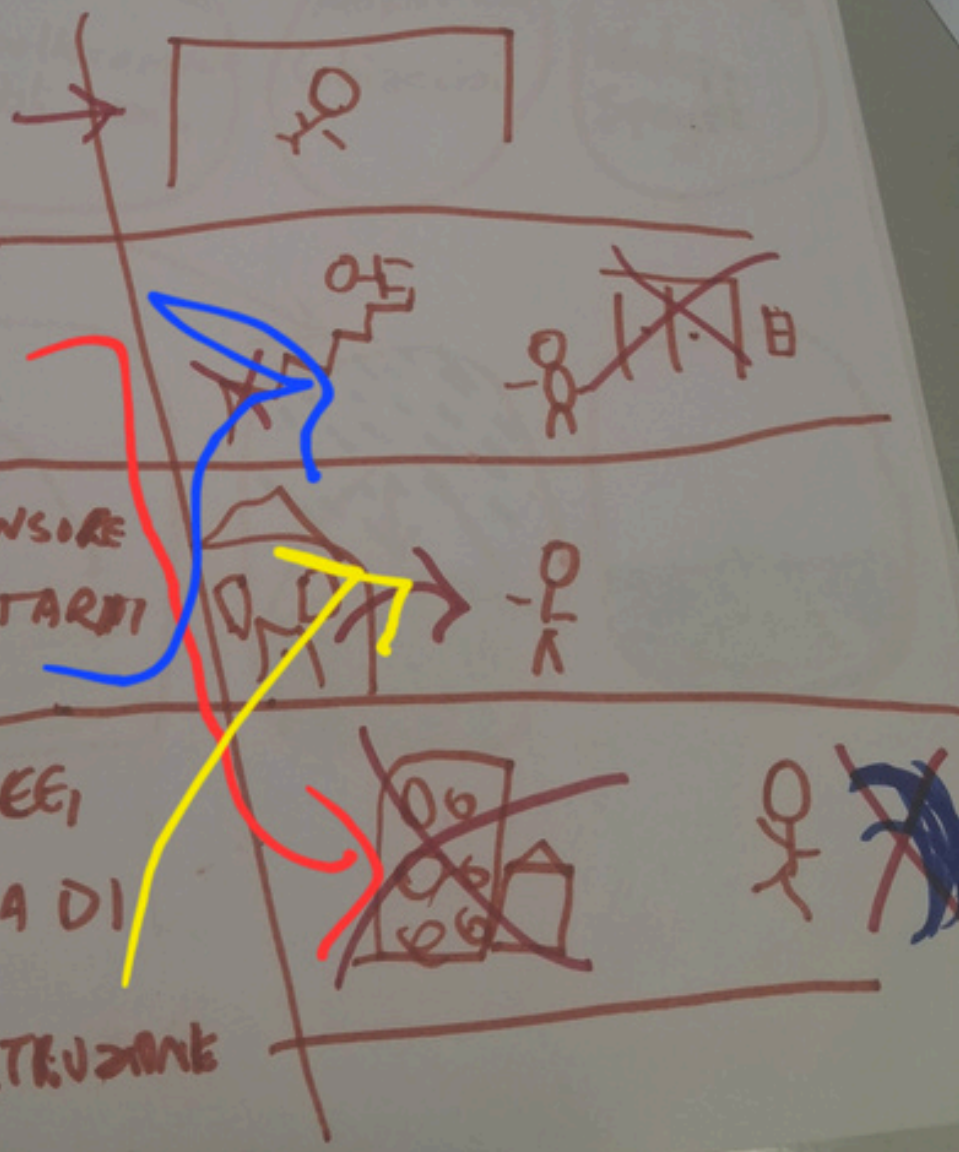

LE COLLINE

Le zone collinarie sono poco meno della metà in Italia.

ESERCIZIO: COLLEGA TESTO A IMMAGINE

STRUTTURALI
Vecchio massiccio erose

TETTONICHE
Sollevamento fondali marini

MORENICHE
Ghiacciai

VULCANICHE
Vulcani Spenti

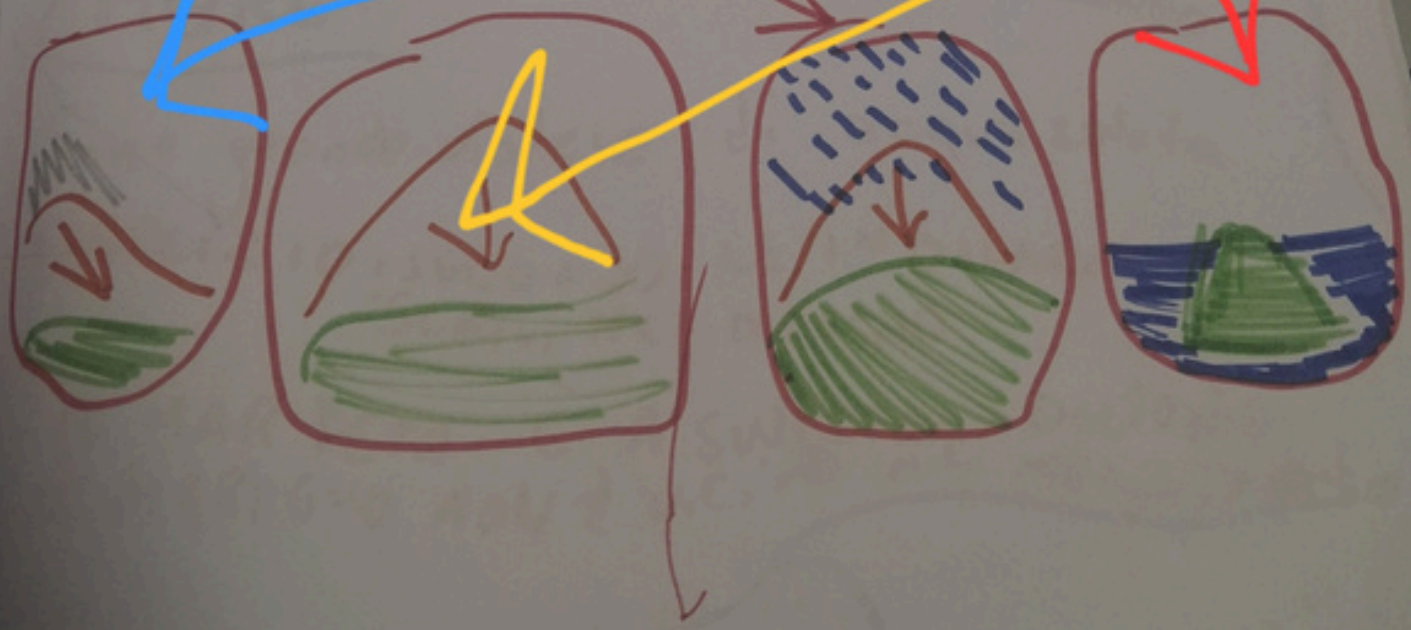

PAESAGGI D'ACQUA

LAGHI

Sono masse di acqua dolce.

ESERCIZIO: OSSERVA IL DISEGNO E SCRIVI IL NOME DEL PIÙ LUNGO: .....



MARE

Sono grande distese di acqua salata.

ESERCIZIO: SECONDO LE INDICAZIONI SCRIVI NEL DISEGNO

- IL MAR FETA È A SINISTRA DELLONIO
- IL MARIGNO NON È VICINO AL MEDITERRANEO



Quaderno degli esercizi

MONTAGNE

ESERCIZIO: FAI IN MODO CHE VALLI GLACIALI DIVENTINO FLUVIALI E VICEVERSA DISEGNANDO

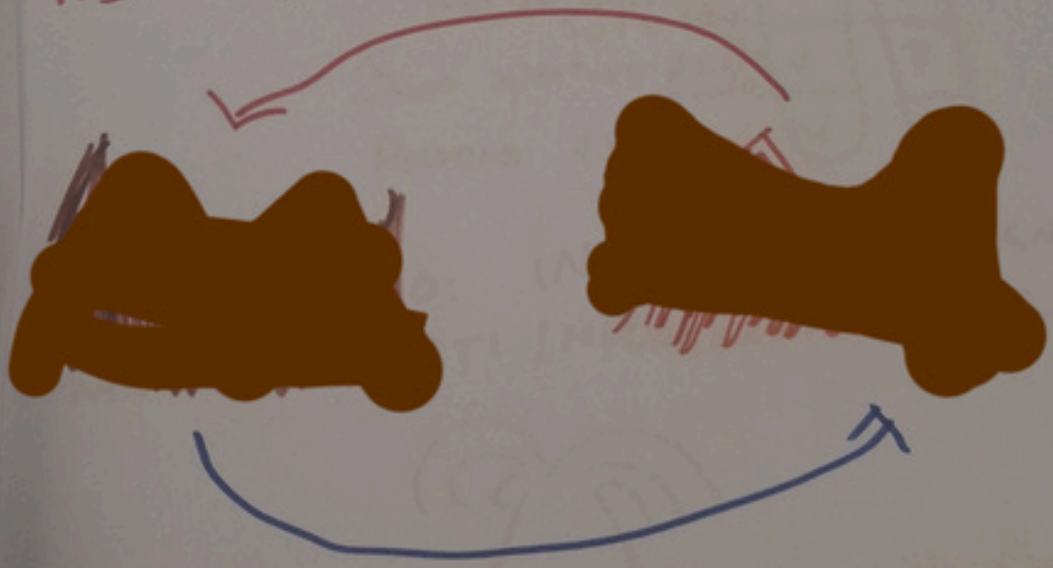

ESERCIZIO: COMPLETA COLLEGANDO

quaderno degli esercizi
TERREMOTI

Riassumi i passaggi. Hai una riga per ogni passaggio.

Nasconditi sotto la porta o un tavolo
Stai lontano da case, mare e palazzi
NO ascensori o andare giù su scale
Esci con calma una volta finito

ERCIZIO: SPOSTA IL QUADRATO GRANDE
LA PUNTA DELLA FRECCIA DISEGNANDO

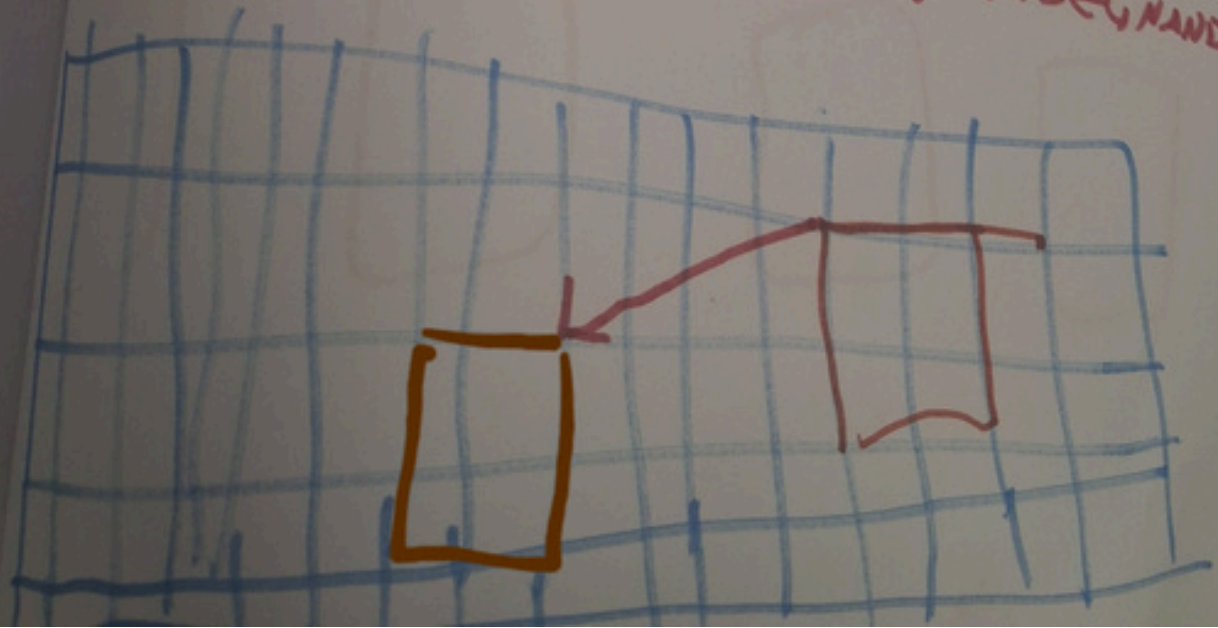

...dernno degli esercizi

COLLINE

...ERCIZIO: SCRIVI NELLE 4 "CASETTE" ...TIPI DI COLLINA E FAI SOTTO UN DISEGNO ADATTO.

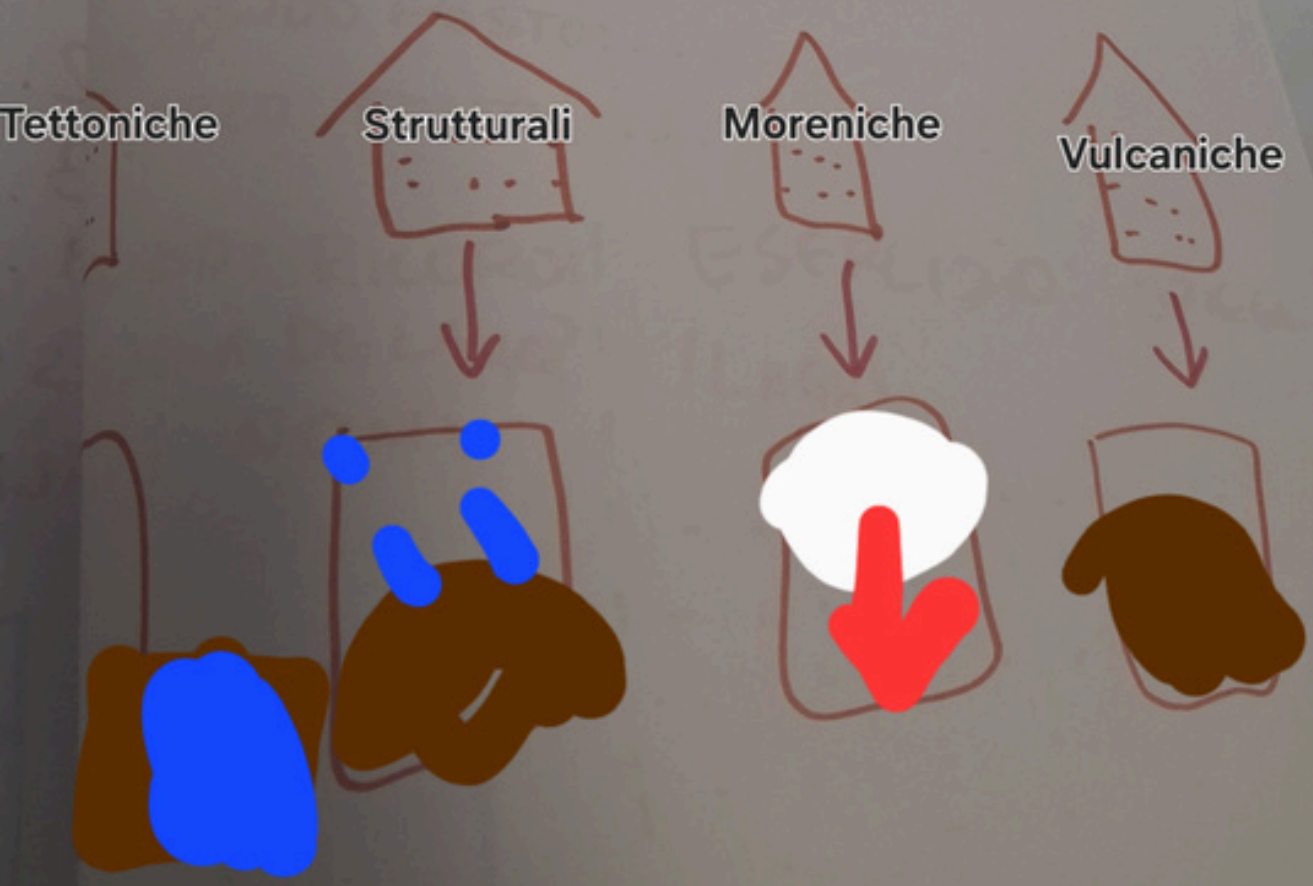

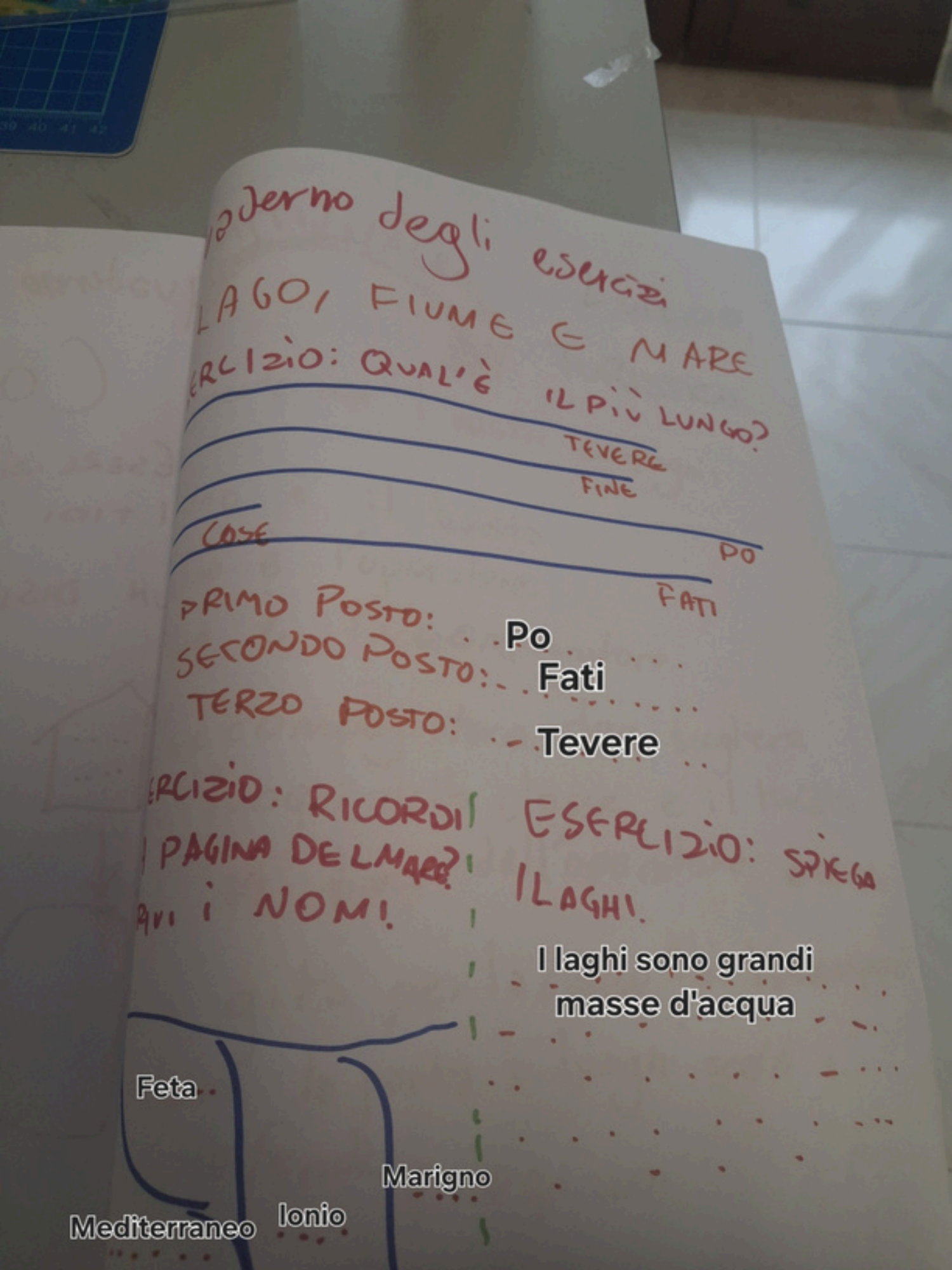
LAGO, FIUME E MARE
ERCIZIO: QUAL'È IL PIÙ LUNGO?
TEVERE
FINE
COSE
PO
FATI
PRIMO POSTO:
SECONDO POSTO:
TERZO POSTO:
Po
Fati
Tevere
ERCIZIO: RICORDI
PAGINA DEL MARE?
I NOMI!
ESERCIZIO: SPIEGA
I LAGHI.
I laghi sono grandi
masse d'acqua
Feta
Marigno
Mediterraneo
Ionio

ATTIVITÀ CREATIVA

L'UFFICIO TURISTICO

Giocate con i vostri compagni:

Uno è il turista
Uno è l'operatore
Uno è l'accompagnatore

L'accompagnatore deve scegliere i luoghi della classe e il turista va al banco dell'operatore e chiede una gita per la classe. Poi l'accompagnatore lo porta ai luoghi scelti e approfondisce ogni uno.

ONTENUTI DIGITALI!

SCANSIONA IL QRCODE

Non puoi inquadrare il qrcode nella versione digitale.

1. INQUADRA IL QR CODE
2. SCEGLI "GEOGRAFIA SIMREM"
3. ACCEDI AI CONTENUTI